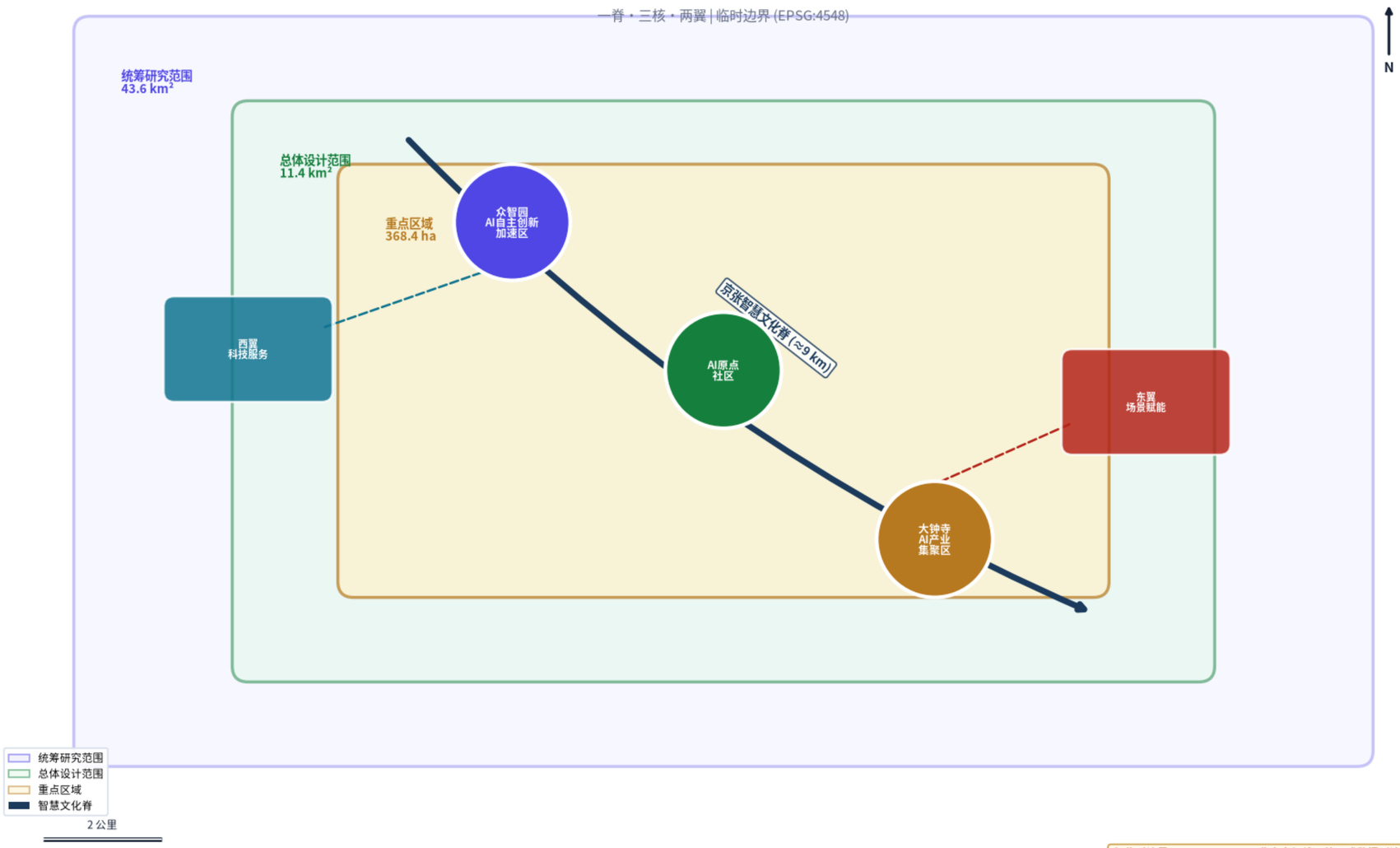
场地: 11,412,825.4 m² | 绿地率: 13.1% | 公共空间率: 1.43%

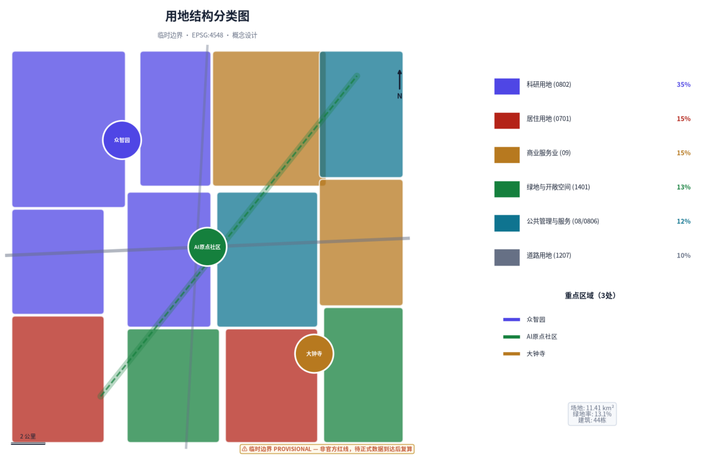
## 京张 · 启元 — 场地区位与三层范围

一脊 · 三核 · 两翼 | 临时边界 (EPSG:4548)



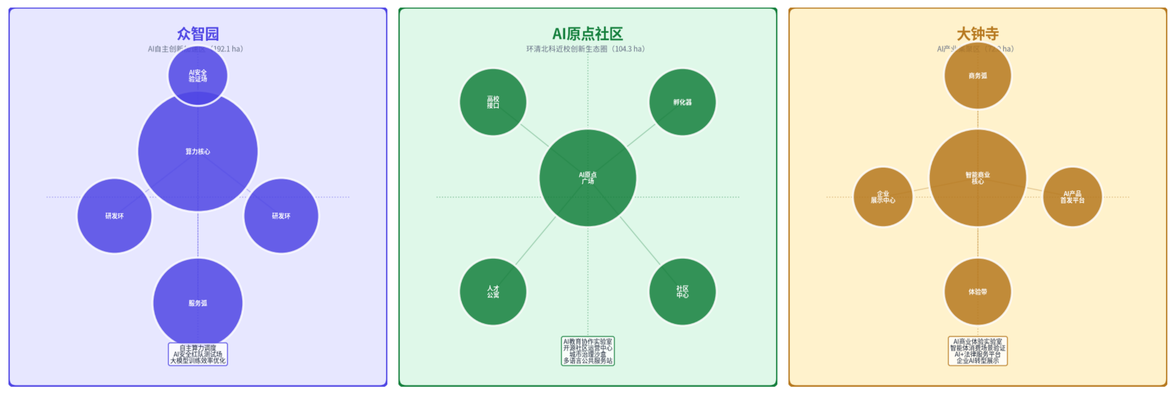

⚠ 临时边界 PROVISIONAL — 非官方红线，待正式数据到达后复算

### 用地结构



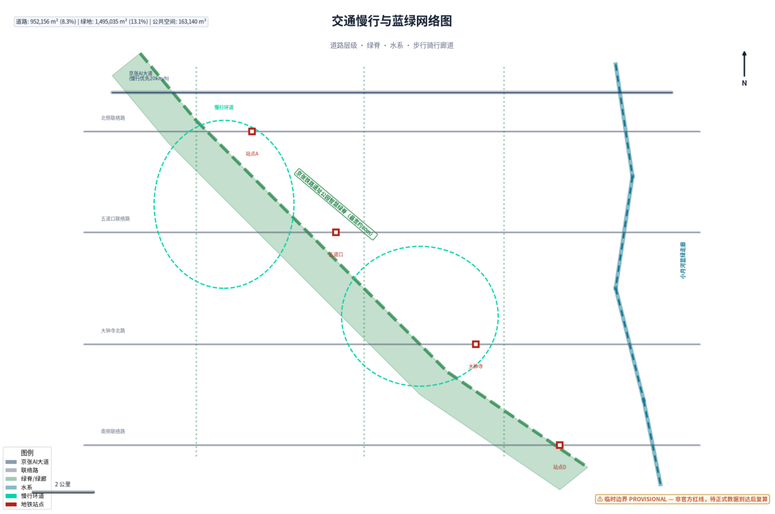

⚠ 临时边界 PROVISIONAL — 非官方红线，待正式数据到达后复算

### 重点区域




⚠ 临时边界 PROVISIONAL — 非官方红线，待正式数据到达后复算

### 交通慢行与蓝绿




⚠ 临时边界 PROVISIONAL — 非官方红线，待正式数据到达后复算

### 指标与证据

#### 核心指标 — 证据链与复算触发条件

EPSG:4548 · 从规划Geo-JSON计算 · 临时边界

| 指标 | 数值 | 公式 | 置信度 | 复算触发条件 |
|---|---|---|---|---|
| 场地面积 | **11,412,825.4 m²** | polygon_area(site_boundary) | 中 | 官方红线发布 |
| 绿地面积 | **1,495,034.6 m²** | sum(area(green_space)) | 中 | 官方边界+用地确认 |
| 绿地率 | **0.131 (13.1%)** | green_area / site_area | 中 | 边界复算 |
| 公共空间 | **163,139.6 m²** | sum(area(public_space)) | 中 | 官方边界+用地确认 |
| 公共空间率 | **0.0143 (1.43%)** | public_space / site_area | 中 | 边界复算 |
| 建筑基底 | **145,944.7 m²** | sum(area(buildings)) | 低 | 建筑普查+红线条件 |
| 建筑密度 | **0.0128 (1.28%)** | footprint / site_area | 低 | 建筑普查+红线条件 |
| 建筑数量 | **44栋** | count(building_features) | 中 | 设计修订 |
| 重点区数量 | **3处** | count(key_area_features) | 高 | 不适用 |
| 道路面积 | **952,156.1 m²** | sum(buffer(centerline,w/2).area) | 低 | 官方道路红线 |

**⚠ 临时性声明**

⚠ 所有数值为临时设计模型量，基于仓库临时粗略边界计算。
这些数值不是官方面积主张。正式几何发布后必须复算。
所有公式使用投影坐标系EPSG:4548（CGCS2000 / 3度带-北京格 CM 117E）。

来源文件: geometry/site_boundary.geojson, geometry/green_space.geojson, geometry/public_space.geojson, geometry/buildings.geojson, geometry/roads.geojson

### 交通慢行与蓝绿




⚠ 临时边界 PROVISIONAL — 非官方红线，待正式数据到达后复算

### 指标与证据

#### 核心指标 — 证据链与复算触发条件

EPSG:4548 · 从规划Geo-JSON计算 · 临时边界

| 指标 | 数值 | 公式 | 置信度 | 复算触发条件 |
|---|---|---|---|---|
| 场地面积 | **11,412,825.4 m²** | polygon_area(site_boundary) | 中 | 官方红线发布 |
| 绿地面积 | **1,495,034.6 m²** | sum(area(green_space)) | 中 | 官方边界+用地确认 |
| 绿地率 | **0.131 (13.1%)** | green_area / site_area | 中 | 边界复算 |
| 公共空间 | **163,139.6 m²** | sum(area(public_space)) | 中 | 官方边界+用地确认 |
| 公共空间率 | **0.0143 (1.43%)** | public_space / site_area | 中 | 边界复算 |
| 建筑基底 | **145,944.7 m²** | sum(area(buildings)) | 低 | 建筑普查+红线条件 |
| 建筑密度 | **0.0128 (1.28%)** | footprint / site_area | 低 | 建筑普查+红线条件 |
| 建筑数量 | **44栋** | count(building_features) | 中 | 设计修订 |
| 重点区数量 | **3处** | count(key_area_features) | 高 | 不适用 |
| 道路面积 | **952,156.1 m²** | sum(buffer(centerline,w/2).area) | 低 | 官方道路红线 |

**⚠ 临时性声明**

⚠ 所有数值为临时设计模型量，基于仓库临时粗略边界计算。
这些数值不是官方面积主张。正式几何发布后必须复算。
所有公式使用投影坐标系EPSG:4548（CGCS2000 / 3度带-北京格 CM 117E）。

来源文件: geometry/site_boundary.geojson, geometry/green_space.geojson, geometry/public_space.geojson, geometry/buildings.geojson, geometry/roads.geojson

| 11.41 km² | 13.1% | 1.43% | 44 | 3 | 12 | 5 | 6 |
|---|---|---|---|---|---|---|---|
| 场地面积 | 绿地率 | 公共空间率 | 建筑 | 重点区 | AI场景 | 地标 | 用户画像 |

临时边界 — 非官方红线，所有指标待正式数据到达后复算。本方案为概念建议，不构成法定规划或投资承诺。